SUPERINTENDENCIA NACIONAL DE ADUANAS Y DE ADMINISTRACIÓN TRIBUTARIA · INTENDENCIA DE ADUANA DE TARAPOTO

MAPA 3 / 3

FRONTERA NORTE Y RED FLUVIAL: DE CONDORCANQUI AL DATEM DEL MARAÑÓN

Escala 1:550 000

Ríos Santiago, Cenepa, Morona, Pastaza, Marañón y Huallaga · puertos, embarcaderos, poblados ribereños y cruces de frontera

Octubre 2026

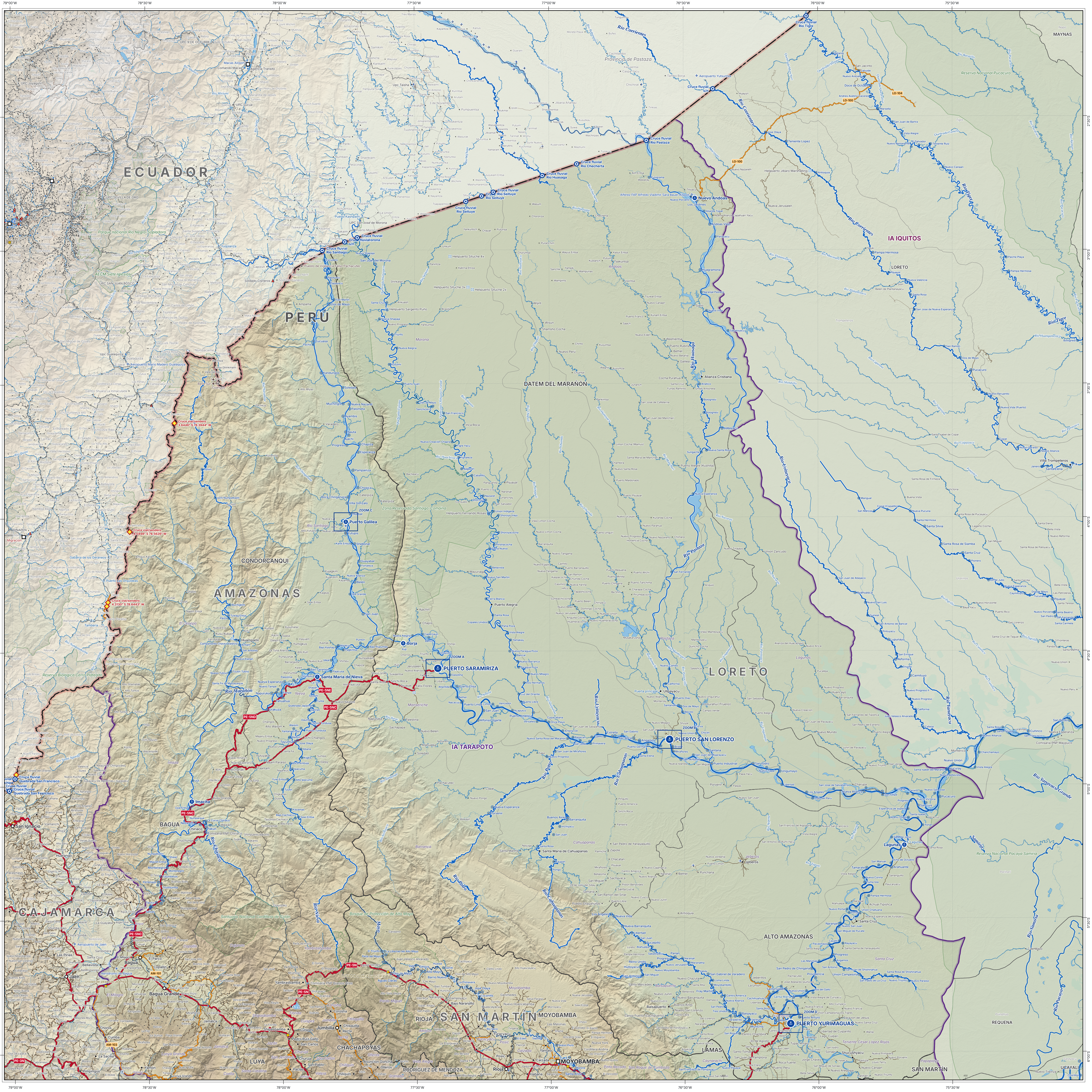

79°00'W
78°30'W
78°00'W
77°30'W
77°00'W
76°30'W
76°00'W
75°30'W
2°30'S
3°00'S
3°30'S
4°00'S
4°30'S
5°00'S
5°30'S
6°00'S
ECUADOR
PERU
AMAZONAS
LORETO
CAJAMARCA
SAN MARTÍN
CONDORCANQUI
DATEM DEL MARAÑÓN
ALTO AMAZONAS
BAGUA
MAYNAS
LORETO
REQUENA
UCAYALI
SAN MARTÍN
MOYOBAMBA
RIOJA
LAMAS
LUYA
CHACHAPOYAS
RODRÍGUEZ DE MENDOZA
IA IQUITOS
IA TARAPOTO
Provincia de Pastaza
Parque nacional Río Negro-Sopladora
AECM Siete Iglesias
Reserva Biológica Cerro Plateado
Reserva Nacional Pucacuro
Reserva Nacional Pacaya Samiria
Zona Reservada Santiago-Comaina
Santuario Nacional Cordillera de Colán
Bosque de Protección de Alto Mayo
Cruce fluvial Río Tigre
Cruce fluvial s/n
Cruce fluvial Río Pastaza
Cruce fluvial Río Checherta
Cruce fluvial Río Huasaga
Cruce fluvial Río Seituye
Cruce fluvial Río Seituye
Cruce fluvial s/n
Cruce fluvial orona
Cruce fluvial Río Santiago
Cruce vial/sendero 3.6446° S 78.3944° W
Cruce vial/sendero 4.0498° S 78.5626° W
Cruce vial/sendero 4.3130° S 78.6443° W
Cruce fluvial Quebrada San Francisco
Cruce fluvial Quebrada San Francisco
Puesto de Vigilancia Falso Pachacutec
Nuevo Andoas
Puerto Galilea
ZOOM C
Borja
PUERTO SARAMIRIZA
ZOOM A
Santa María de Nieva
Imacita
PUERTO SAN LORENZO
ZOOM B
Lagunas
PUERTO YURIMAGUAS
ZOOM D
Río Corrientes
Río Tigre
Río Pastaza
Río Huasaga
Río Santiago
Río Marañón
Río Nieva
Río Cahuapanas
Río Potro
Río Urituyacu
Río Yanayacu
Río Yanayacu Grande
Río Samiria
Río Pacaya
Río Chiriaco
Mayo
Morona
Alianza Cristiana
Ullpayacu
Santa Cruz
Jeberos
Iquitos
Villa Trompeteros
Bagua
Bagua Grande
Jaén
San Ignacio
MOYOBAMBA
Rioja
PE-5N
PE-5NC
PE-5NE
PE-5ND
PE-3N
AM-101
AM-103
LO-100
LO-104

ZOOM A · Puerto de Saramiriza – río Marañón

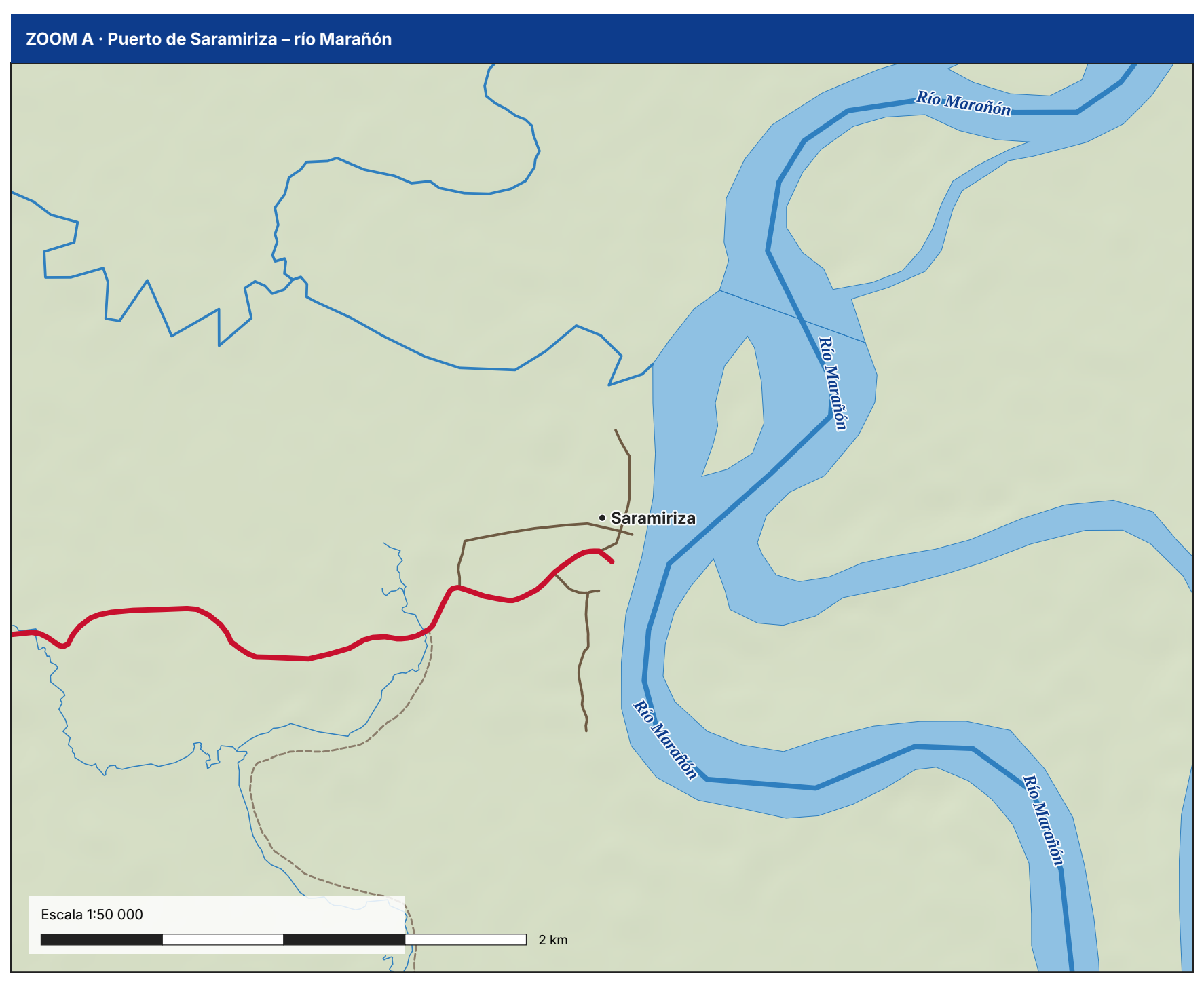

Río Marañón
Río Marañón
Río Marañón
Río Marañón
Saramiriza
Escala 1:50 000
2 km

ZOOM B · Puerto de San Lorenzo – río Marañón

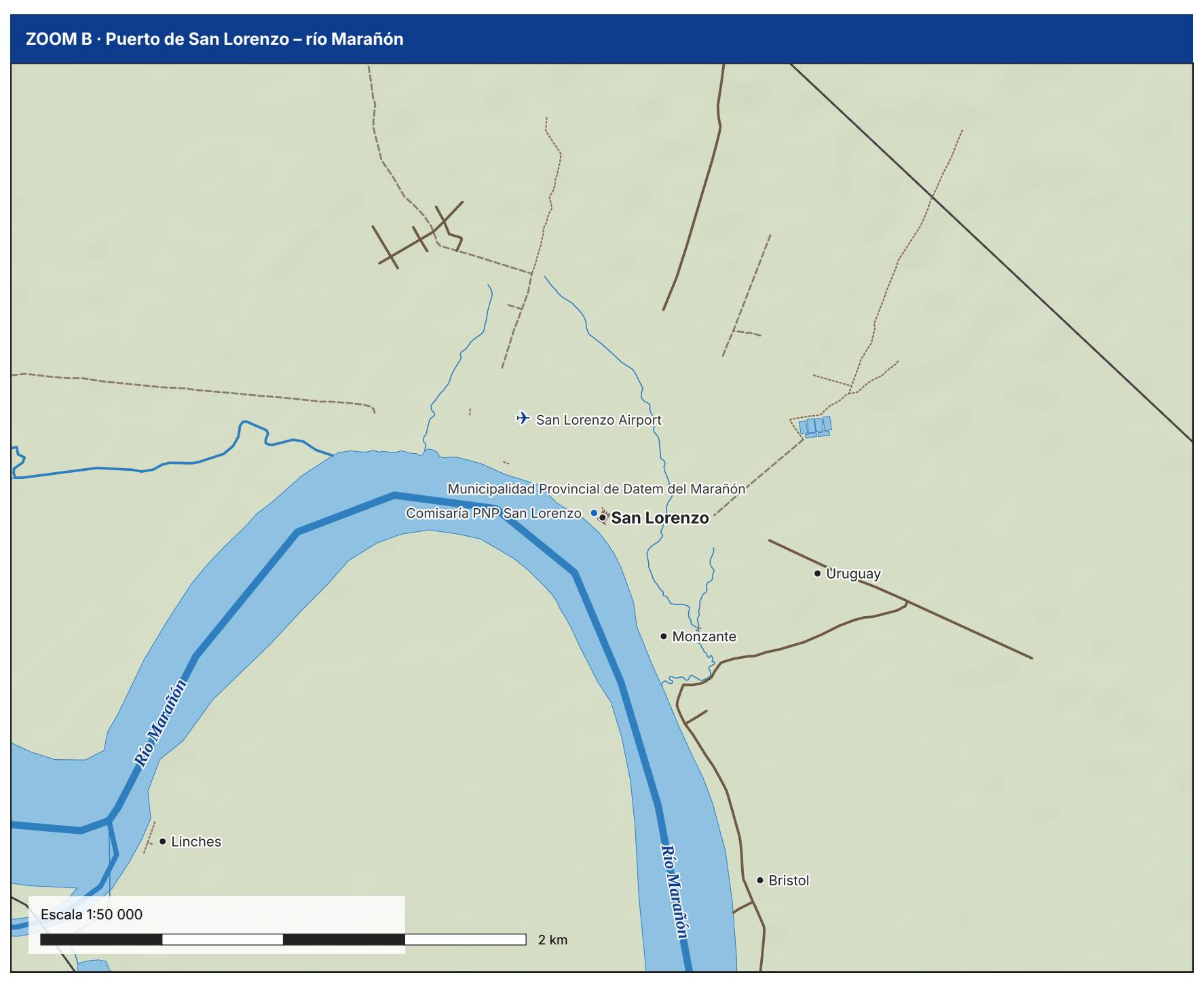

San Lorenzo Airport
Municipalidad Provincial de Datem del Marañón
Comisaría PNP San Lorenzo
San Lorenzo
Uruguay
Monzante
Río Marañón
Río Marañón
Linches
Bristol
Escala 1:50 000
2 km

ZOOM C · Puerto Galilea – río Santiago

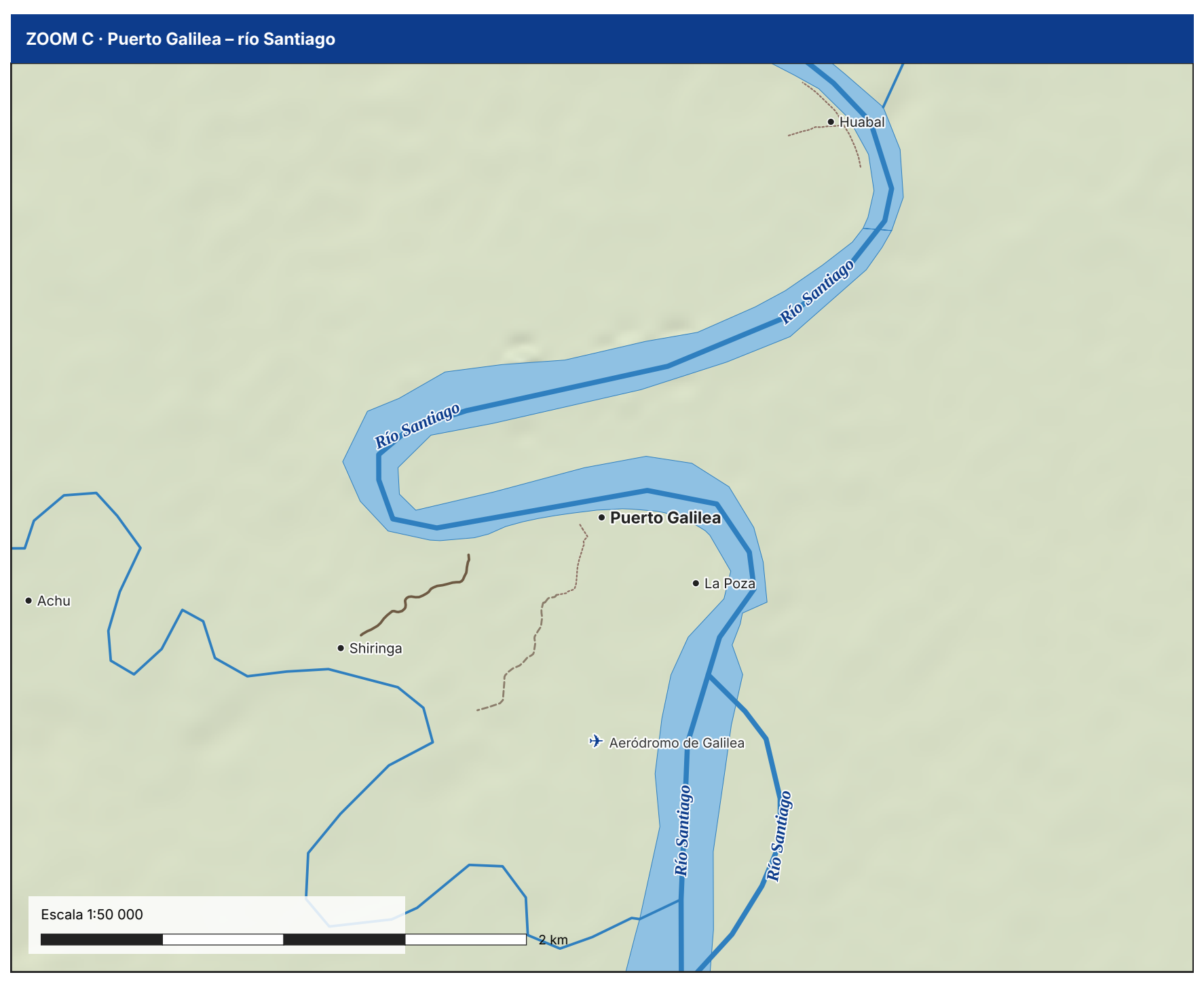

Huabal
Río Santiago
Río Santiago
Puerto Galilea
La Poza
Achu
Shiringa
Aeródromo de Galilea
Río Santiago
Río Santiago
Escala 1:50 000
2 km

ZOOM D · Puerto de Yurimaguas – río Huallaga

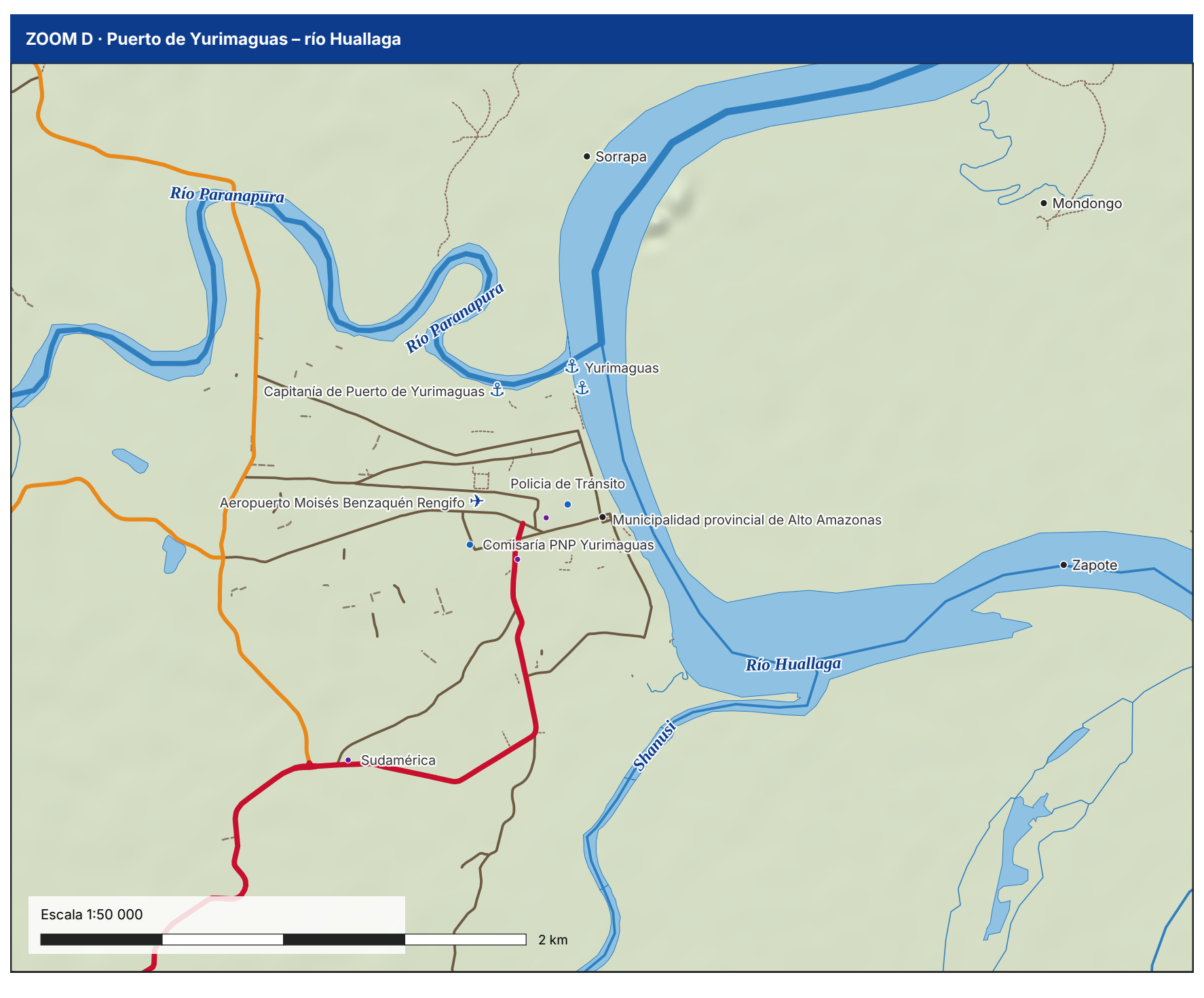

Sorrapa
Mondongo
Río Paranapura
Río Paranapura
Yurimaguas
Capitanía de Puerto de Yurimaguas
Policía de Tránsito
Aeropuerto Moisés Benzaquén Rengifo
Municipalidad provincial de Alto Amazonas
Comisaría PNP Yurimaguas
Zapote
Río Huallaga
Shanusi
Sudamérica
Escala 1:50 000
2 km

FRONTERA Y CONTROL

- Límite internacional Perú – Ecuador
- ◇ Cruce vial o de sendero con la frontera (OSM)
- ○ Cruce fluvial de la frontera
- ● Control fronterizo / Migraciones / SUNAT
- ▲ Puesto de control / vigilancia (OSM)
- + Puesto o base militar en territorio peruano (OSM)

RED FLUVIAL

- Vía navegable principal (Hidrovía Amazónica)
- Río navegable por embarcaciones menores
- Río / quebrada
- Ruta de transbordo / ferry (OSM)
- ● Puerto fluvial principal
- ● Puerto / embarcadero secundario
- ● Poblado ribereño (a < 1,5 km de río navegable)

VÍAS Y LÍMITES

- Red vial nacional / departamental
- Red vial vecinal / trocha
- Sendero / camino peatonal (OSM)
- Circunscripción IA Tarapoto / otras IA
- Límite departamental / provincial
- Límite distrital (referencial INEI)
- 🟩 Área natural protegida

ESCALA GRÁFICA

10 0 10 20 30 40 50 km

N

WGS 84 · UTM Zona 18 Sur (EPSG:32718) · Escala 1:550 000 · A0 vertical
Todo el territorio peruano representado pertenece a la ZTE (Ley N.° 27037, art. 3).
Ríos, puertos, poblados, vías, senderos, cruces y puntos de control: © OpenStreetMap (30.10.2026).
Cruces de frontera: intersección de vías/senderos/ríos OSM con el límite INEI (referencial).
Límites: INEI 2019 (referenciales). Relieve: AWS Terrain Tiles.
Capa opcional de casos por distrito: pendiente de datos agregados del equipo.
Elaborado por: Equipo de Gestión de Riesgo – IA Tarapoto